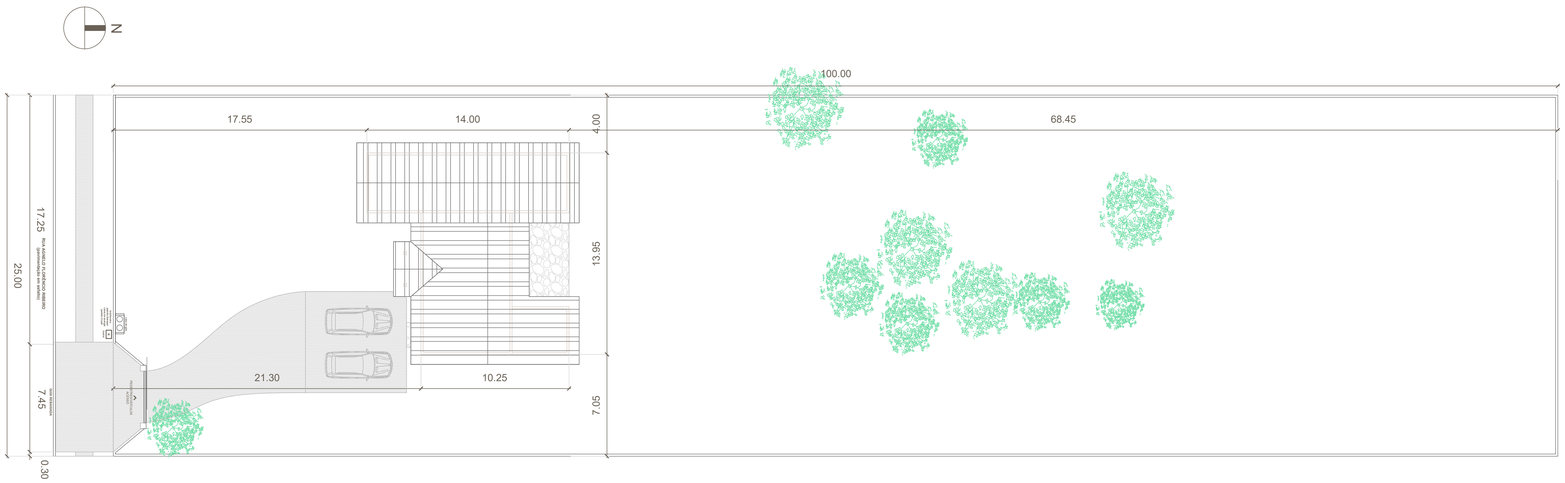

Implantação
escala 1:150

LEGENDA ACABAMENTOS

	ACABAMENTOS - PAREDE
A1	PORCELANATO
A2	PINTURA SOBRE MASSA CORRIDA
A3	PINTURA PROJETADA
	ACABAMENTOS - TETO
B1	LAJE COM PINTURA SOBRE MASSA CORRIDA
B2	FORRO DE DRYWALL COM PINTURA SOBRE MASSA CORRIDA
B3	FORRO DE MADEIRA SOB TELHADO
	ACABAMENTOS - PISO
C1	PORCELANATO
C2	PISO LAMINADO
C3	PISO EM PEDRA

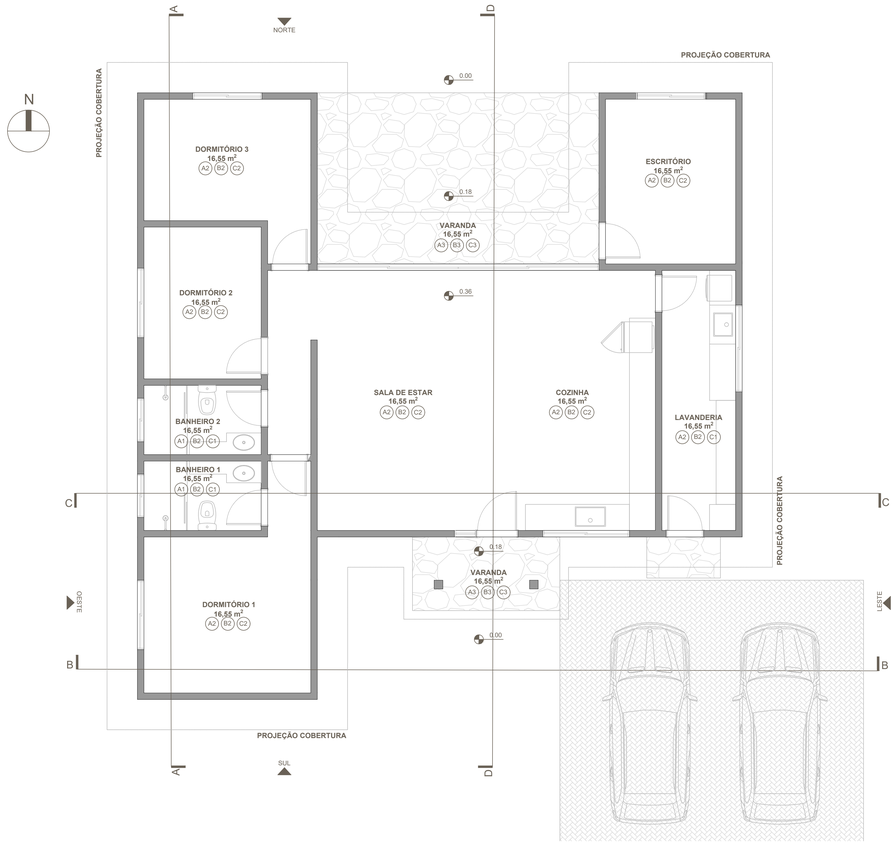

Planta - Pavimento térreo
escala 1:50

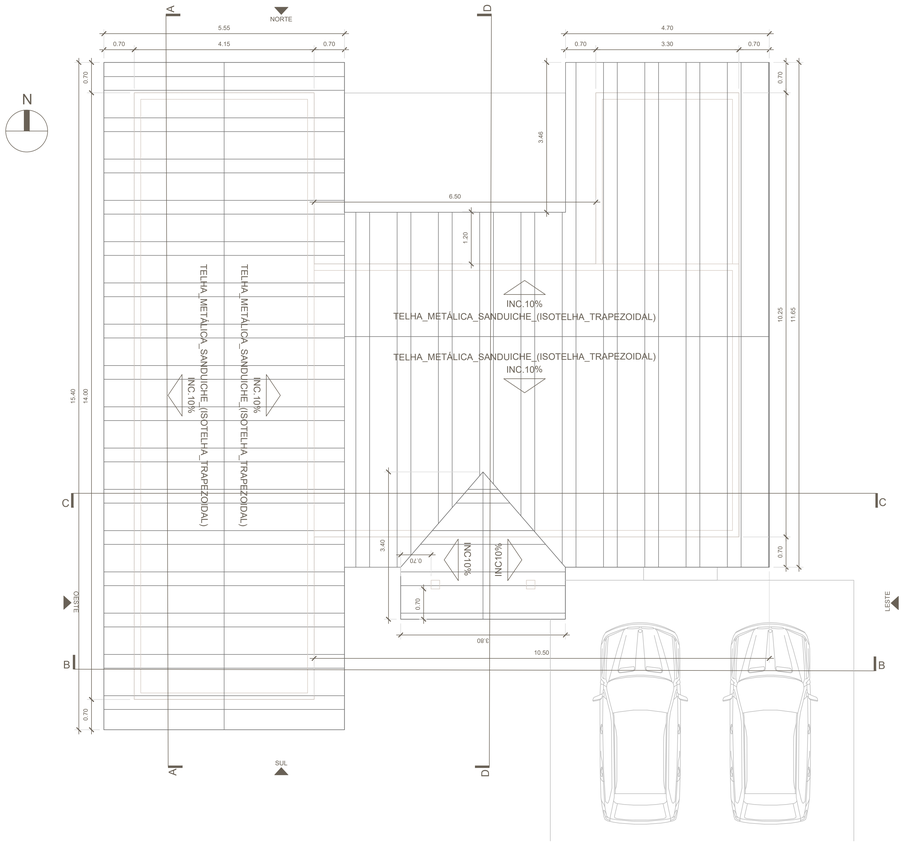

Planta - Cobertura
escala 1:50

SITUAÇÃO

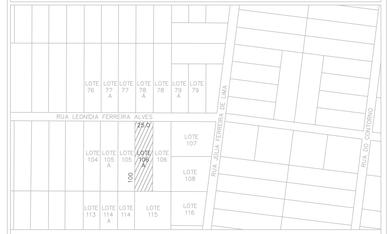

SITUAÇÃO - Escala 1:3.000

LOTE	QUADRA	PLANTA	INDICAÇÃO FISCAL
106-A	N/A	JARDIM DAS ACÁCIAS	02.01.01.009.0916-0

QUADRO DE AREAS DO LOTE

DADOS DO LOTE	
A) ÁREA TOTAL A SER CONSTRUÍDA	138,90 m²
QUADRO DE AREAS	
ÁREA DO LOTE	2.500,00 m²

QUADRO DE AREAS	
DADOS DA CONSTRUÇÃO	
A) ÁREA A SER CONSTRUÍDA	138,90 m²
QUADRO DE AREAS - ÁREA ÚTIL	
SALA DE ESTAR	28,80 m2
COZINHA	18,00 m2
LAVANDERIA	10,20 m2
ESCRITÓRIO	11,40 m2
CORREDOR	4,22 m2
DORMITÓRIO 1 (SUÍTE)	15,60 m2
DORMITÓRIO 2	9,47 m2
DORMITÓRIO 3	11,77 m2
BANHEIRO 1 (SUÍTE)	4,32 m2
BANHEIRO 2	4,32 m2

ESTATÍSTICA GERAL	
DADOS DO LOTE	
A) ÁREA DO LOTE	2.500,00 m2
ÁREAS A CONSTRUIR E CONSTRUÍDAS	
ÁREA TOTAL A SER CONSTRUÍDA	138,90 m²
ÁREA A SER CONSTRUÍDA - TÉRREO	138,90 m²
ÁREA DE PROJEÇÃO	186,60 m²
ÁREA PERMEÁVEL	2210,23 m2
PARÂMETROS/ OUTROS	
TAXA DE OCUPAÇÃO	5,55%
TAXA DE PERMEABILIDADE	88,40%
COEFICIENTE DE APROVEITAMENTO	0,05
ALTURA MÁXIMA	5,08 m
RECUO FRONTAL	17,55 m
NÚMERO DE PAVIMENTOS	01
NÚMERO DE UNIDADES	01
Nº DE VAGAS DE ESTACIONAMENTO	02

INFRAESTRUTURA	
DADOS DO LOTE	
REDE PÚBLICA DE ESGOTO	RECEBE - VIA SANEPAR
PAVIMENTAÇÃO	VIA PAVIMENTADA - ASFALTO
GALERIA DE AGUA PLUVIAL	EXISTENTE
REDE ELÉTRICA	RECEBE - VIA CORELS
REDE DE AGUA POTÁVEL	RECEBE - VIA SANEPAR

NOTAS

1. TODAS AS COTAS, MEDIDAS E ÁREAS, BEM COMO O ATENDIMENTO AO CÓDIGO DE OBRAS, SÃO DE INTEIRA RESPONSABILIDADE DO AUTOR DO PROJETO ARQUITETÔNICO
2. O PROJETO ESTÁ RIGOROSAMENTE DE ACORDO COM AS NORMAS TÉCNICAS E COM AS DISPOSIÇÕES LEGAIS EM VIGOR DO MUNICÍPIO DE QUATRO BARRAS – PR.
3. O PROPRIETÁRIO E RESPONSÁVEL TÉCNICO ESTÃO CIENTES DAS PENALIDADES PREVISTAS NA LEGALIZAÇÃO MUNICIPAL QUANTO ÀS INFRAÇÕES E SUAS DISPOSIÇÕES, ESPECIALMENTE NO QUE TANGE INFORMAÇÕES NO ATENDIMENTO AO CÓDIGO DE OBRAS, E A EXECUÇÃO DA OBRA EM DESCONFORMIDADE COM O PROJETO APROVADO.

"O AUTOR DO PROJETO E O RESPONSÁVEL TÉCNICO SÃO RESPONSÁVEIS CIVIL E ADMINISTRATIVAMENTE PELO ATENDIMENTO DAS ESPECIFICAÇÕES CONSTANTES NOS ANEXOS DA LEI COMPLEMENTAR 40/2023, DA LEGISLAÇÃO MUNICIPAL E NORMAS BRASILEIRAS VIGENTES, SUJEITANDO-SE ÀS SANÇÕES LEGAIS DECORRENTES DE EVENTUAIS PREJUÍZOS A TERCEIROS."

USO EXCLUSIVO DA PREFEITURA

NUMERO DA REVISÃO	DATA DE ENTREGA	DATA DA REVISÃO	DATA DA RETIRADA
000	mar/2026		

KANTI ARQUITETURA
tatianamoritanobre@gmail.com
Fone: (41) 99181-1888

Descrição:
CONSTRUÇÃO DE RESIDÊNCIA UNIFAMILIAR EM ALVENARIA

Referência:
PLANTA DE IMPLANTAÇÃO
PLANTA PAVIMENTO TÉRREO
PLANTA DE COBERTURA
ESTATÍSTICA

Escala:
GERAL/POR DESENHO

Date:
03 / 2026

Desenho:
TATIANA MORITA NOBRE MATTOS
tatianamoritanobre@gmail.com
Fone: (41) 99181-1888

PROJETO ARQUITETÔNICO

Autor do projeto / Responsável técnico: TATIANA MORITA NOBRE MATTOS	CAU/PR: A42624-5	Assinatura:
Responsável pela execução:	CREA/PR:	Assinatura:
Proprietária(s): JORGYANO BRUNO DE OLIVEIRA VIEIRA	CPF: 061.044.724-60	Assinatura:
Proprietária(s):	CNPJ:	Assinatura:

Importante:
ESTE PROJETO NÃO PODERÁ SER REPRODUZIDO PARA OUTROS FINS SEM A EXPRESSA AUTORIZAÇÃO DO RESPONSÁVEL TÉCNICO ACIMA DESCRITO

Prancha:
01/02

FOLHA A0